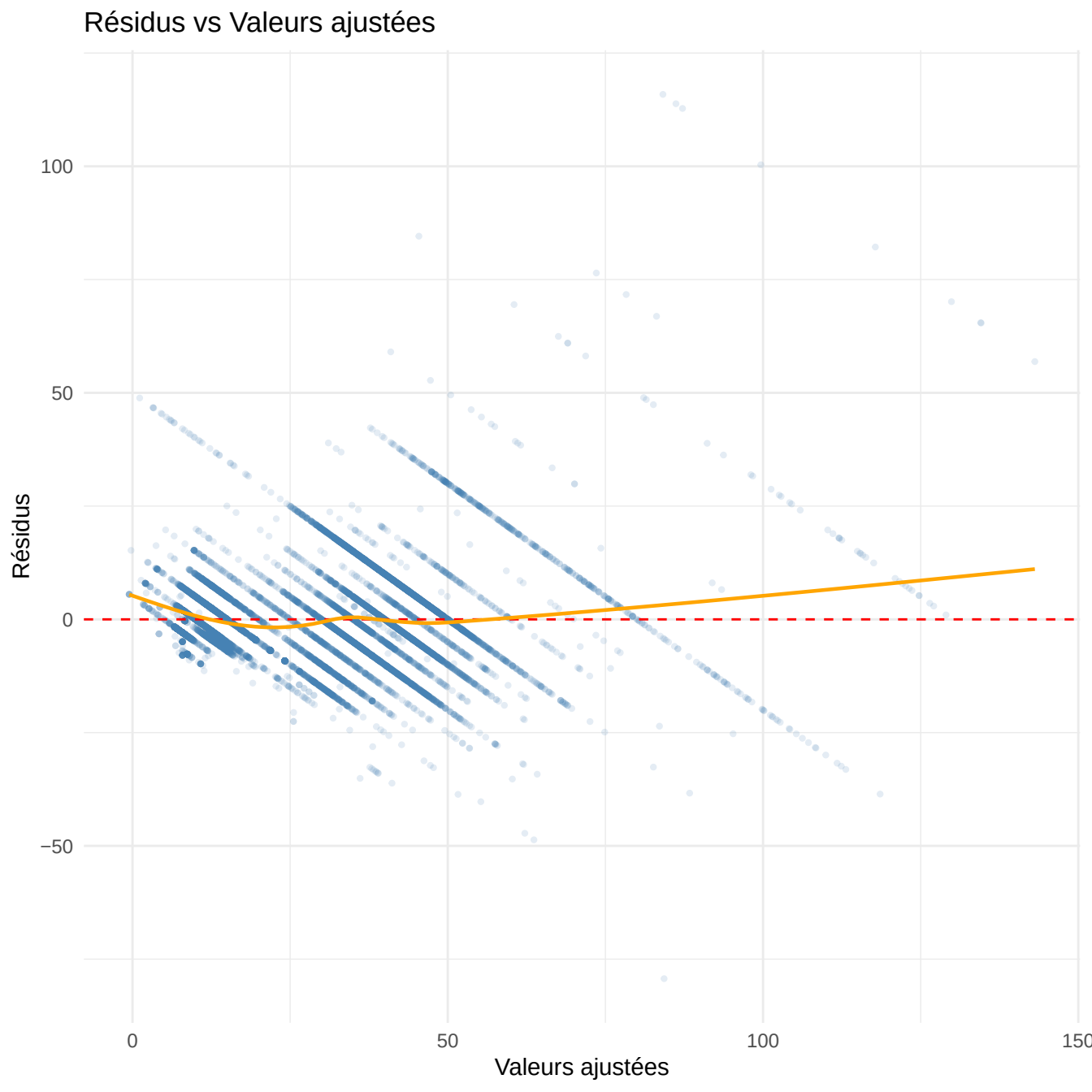
Résidus vs Valeurs ajustées
Résidus
Valeurs ajustées
100
50
0
−50
0
50
100
150

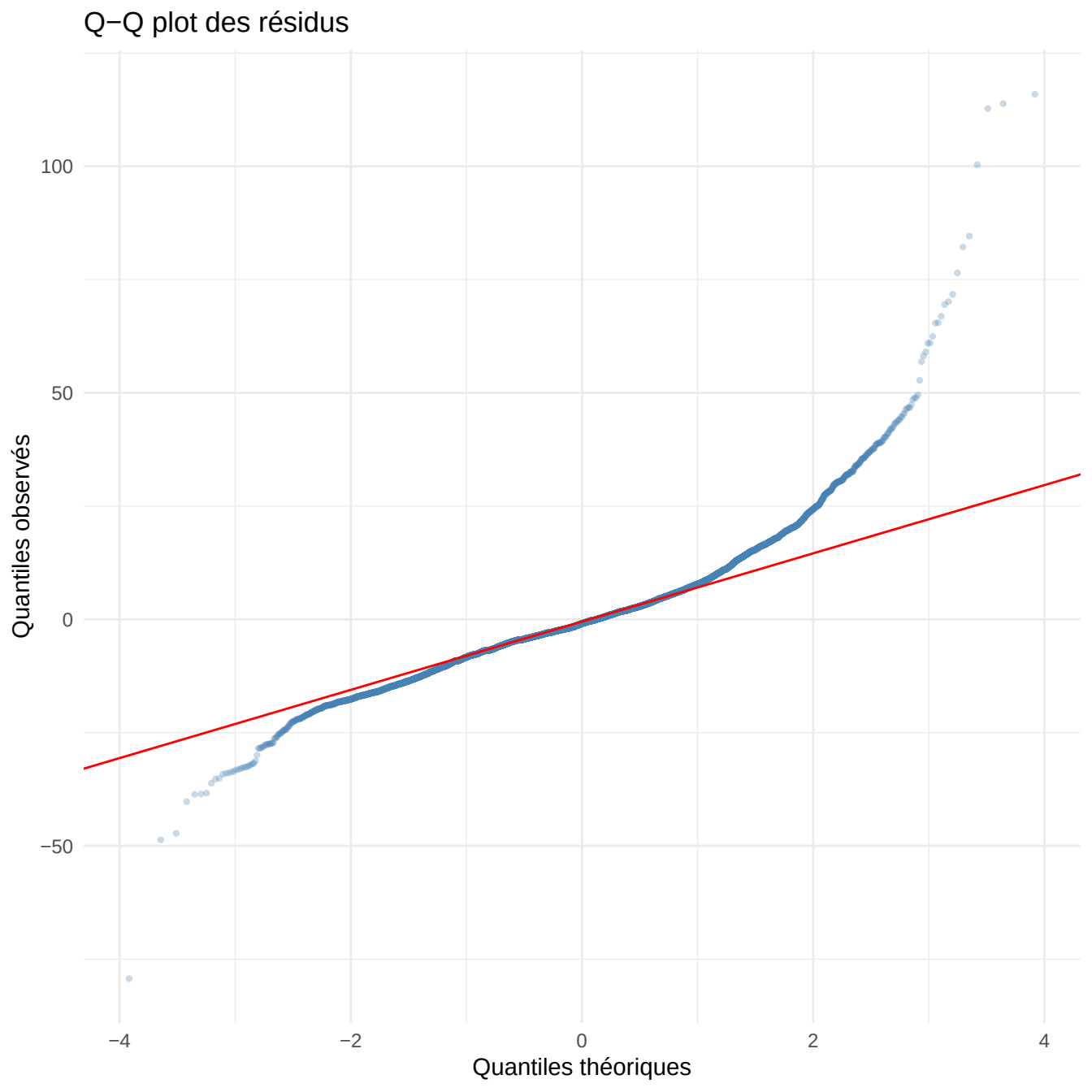
Q−Q plot des résidus
100
50
0
−50
Quantiles observés
−4
−2
0
2
4
Quantiles théoriques

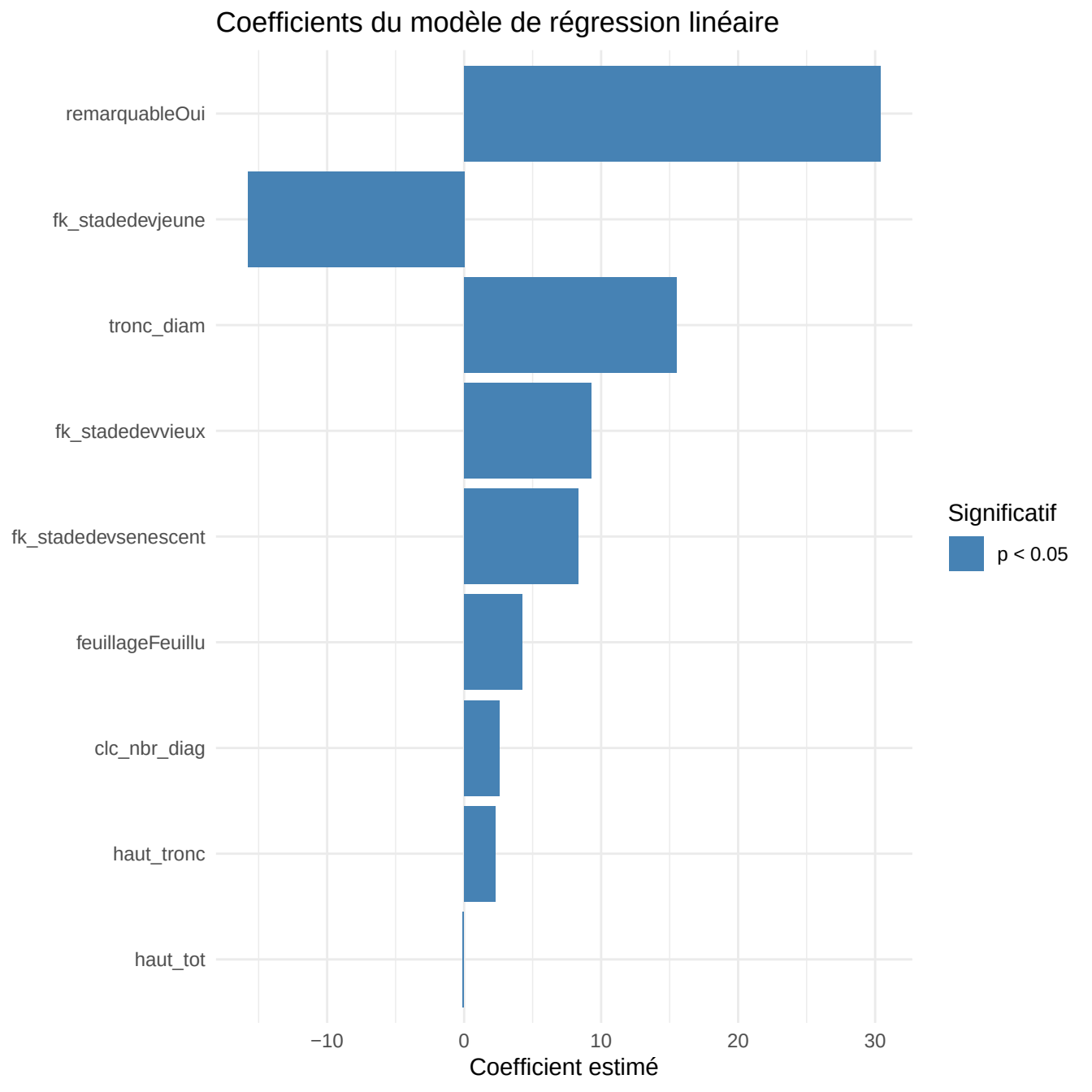
Coefficients du modèle de régression linéaire
remarquableOui
fk_stadedevjeune
tronc_diam
fk_stadedevvieux
fk_stadedevsenescent
feuillageFeuillu
clc_nbr_diag
haut_tronc
haut_tot
−10
0
10
20
30
Coefficient estimé
Significatif
p < 0.05

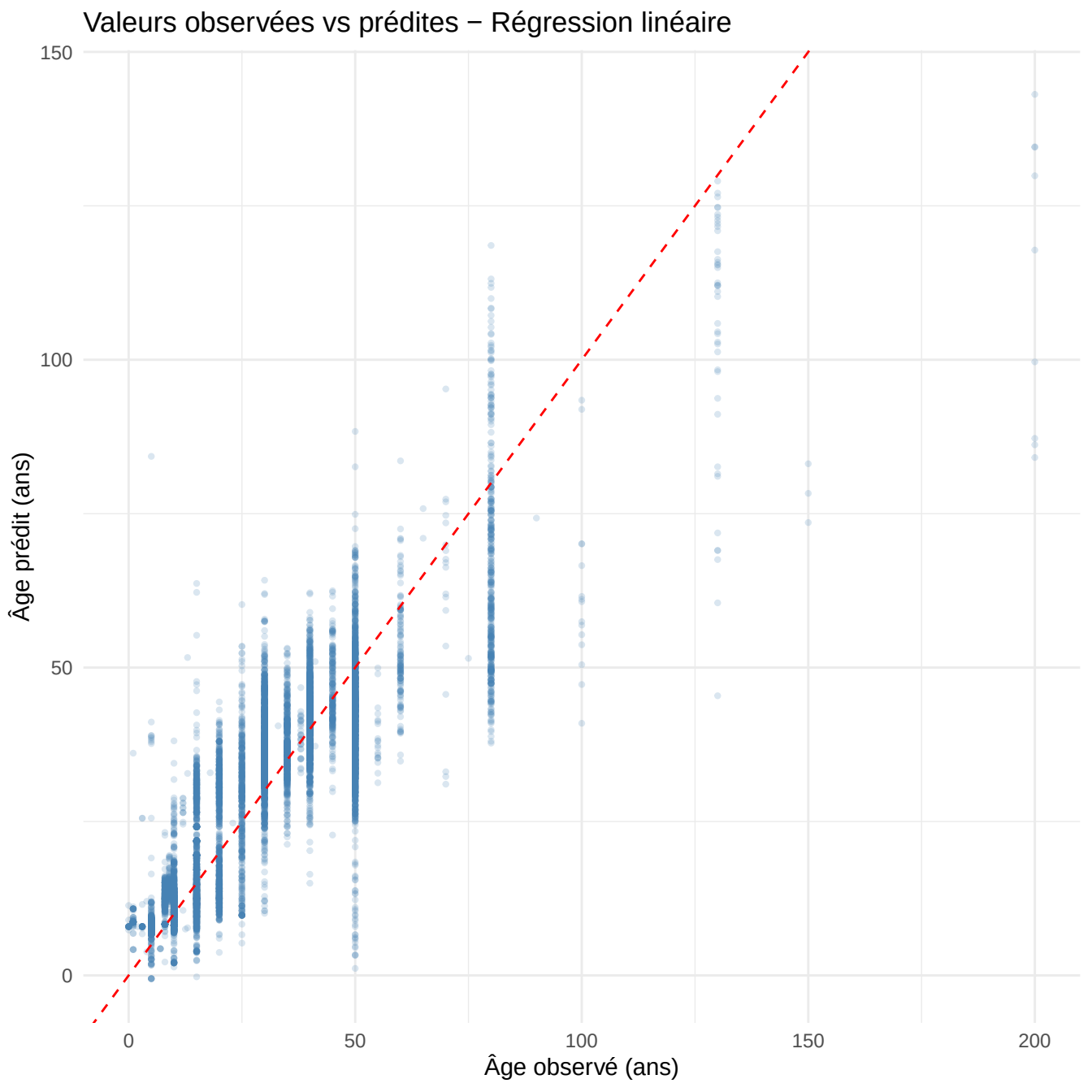
Valeurs observées vs prédites − Régression linéaire
150
100
50
0
Âge prédit (ans)
0
50
100
150
200
Âge observé (ans)

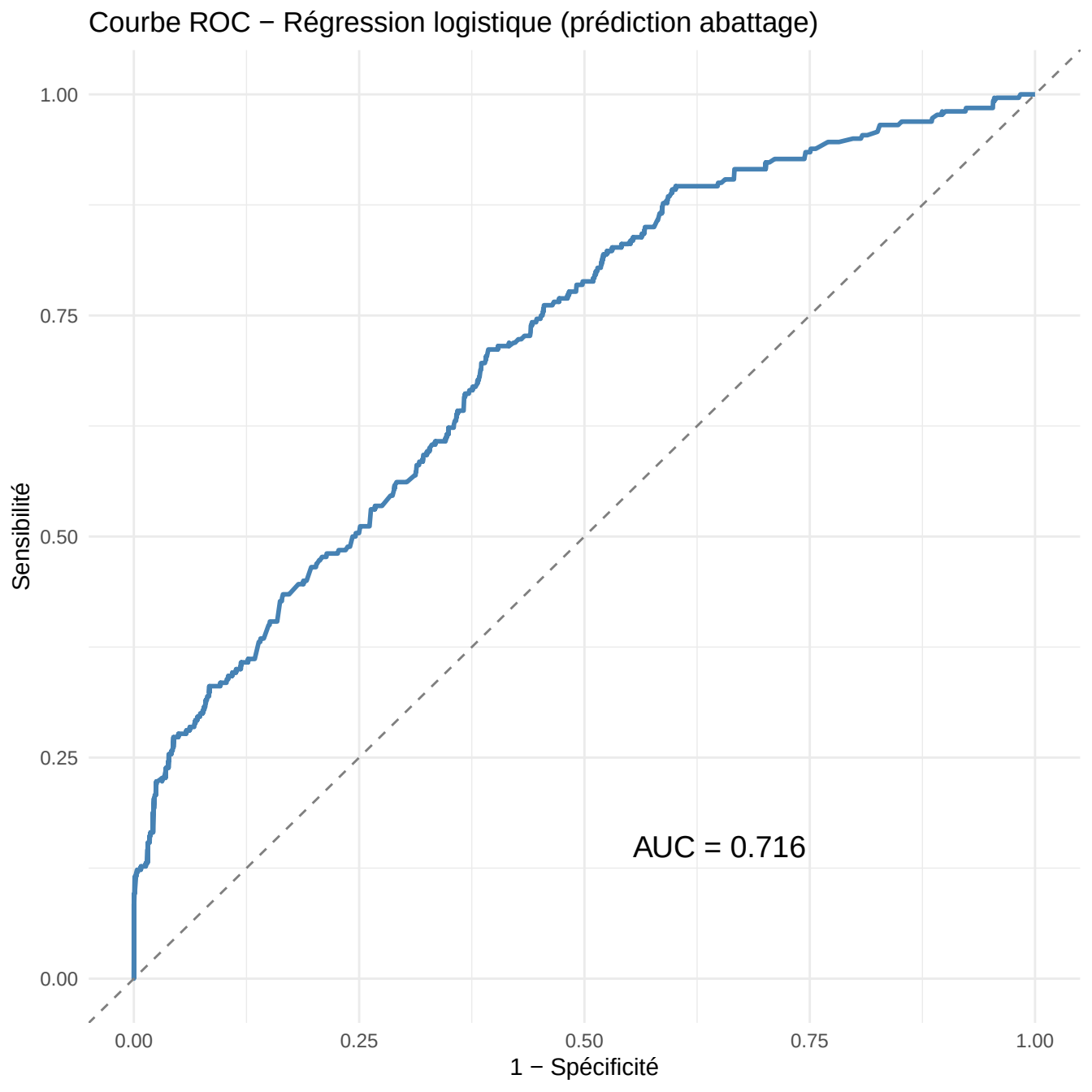
Courbe ROC − Régression logistique (prédiction abattage)
Sensibilité
1 − Spécificité
0.00
0.25
0.50
0.75
1.00
AUC = 0.716

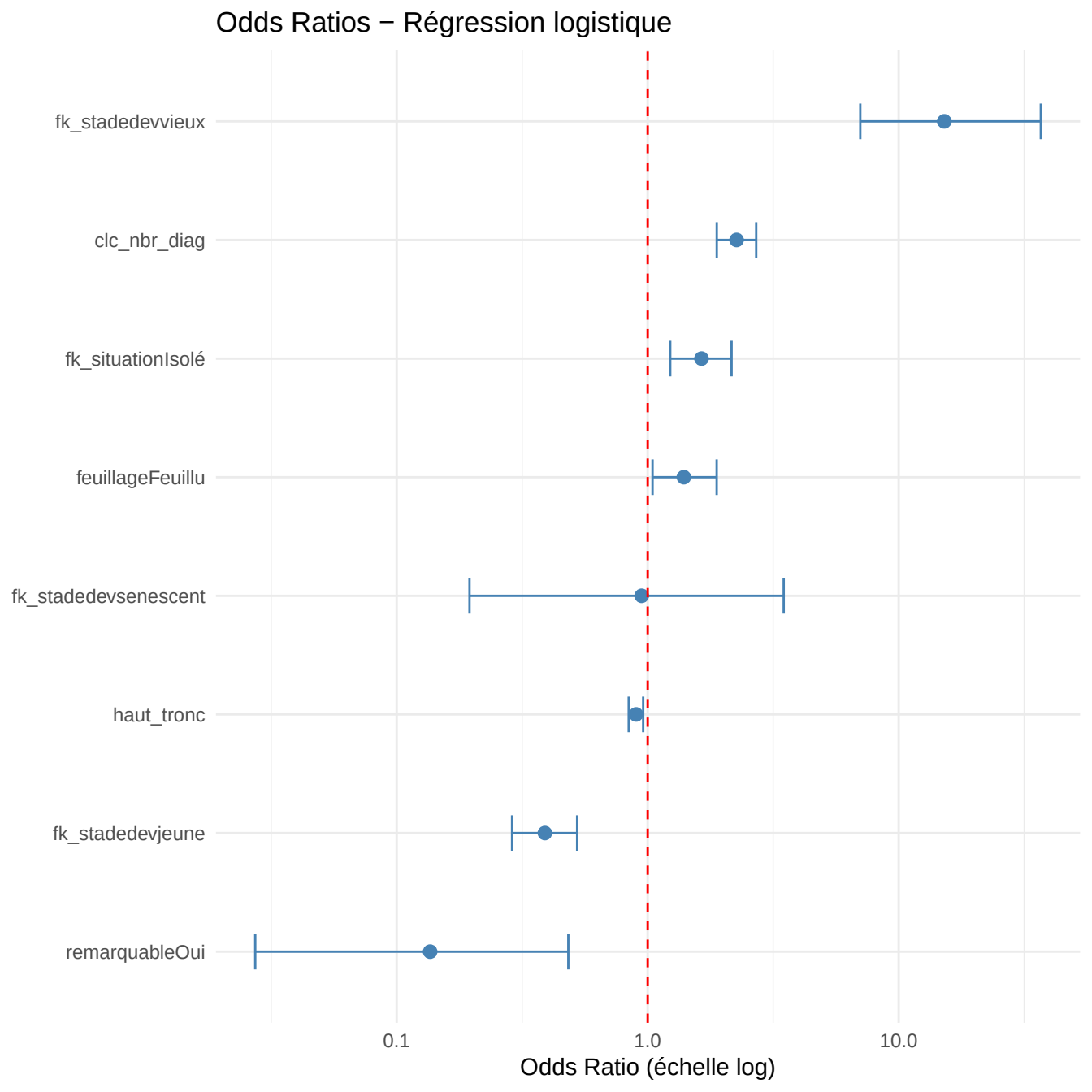
Odds Ratios − Régression logistique
fk_stadedevvieux
clc_nbr_diag
fk_situationIsolé
feuillageFeuillu
fk_stadedevsenescent
haut_tronc
fk_stadedevjeune
remarquableOui
0.1
1.0
10.0
Odds Ratio (échelle log)

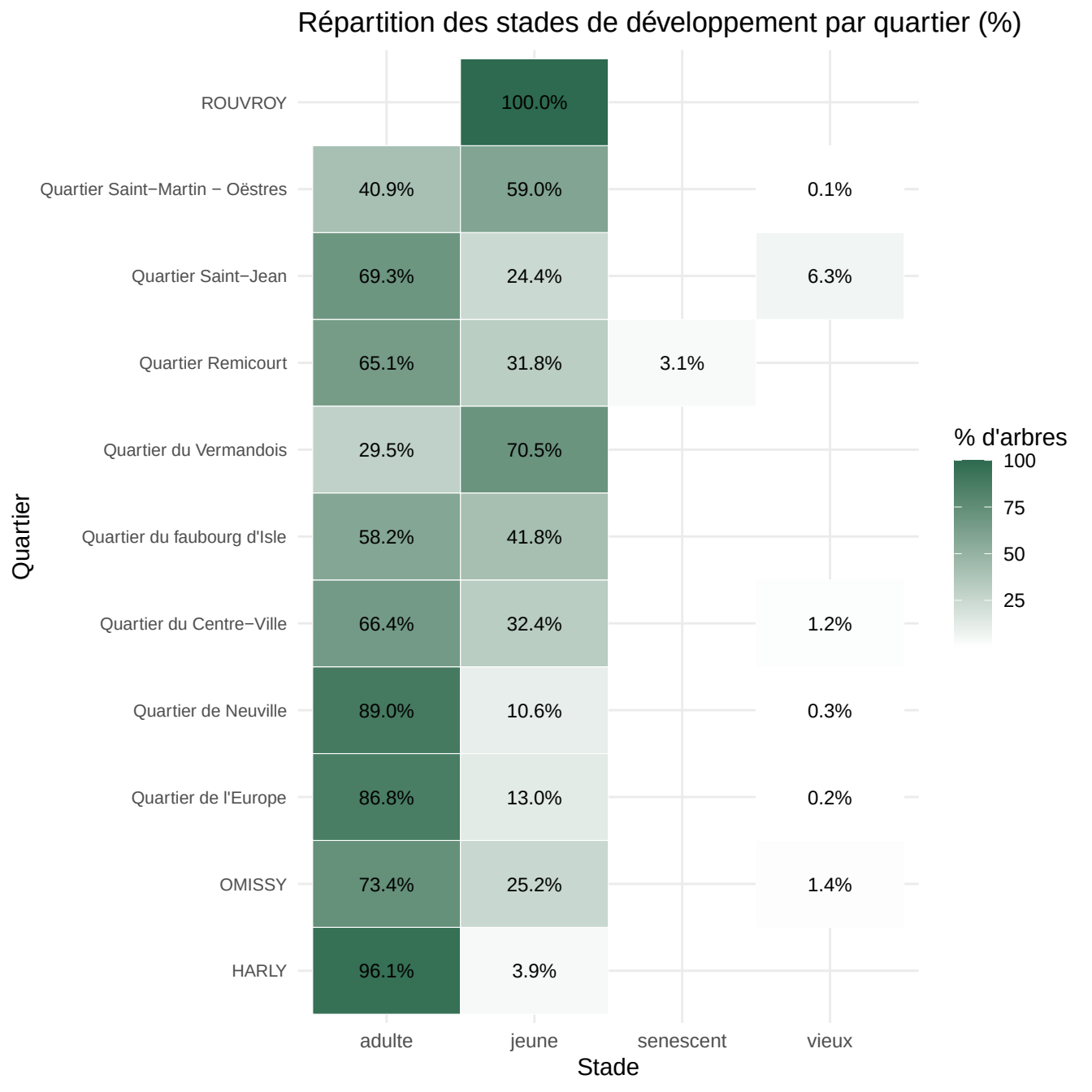
Répartition des stades de développement par quartier (%)
ROUVROY
100.0%
Quartier Saint−Martin − Oëstres
40.9%
59.0%
0.1%
Quartier Saint−Jean
69.3%
24.4%
6.3%
Quartier Remicourt
65.1%
31.8%
3.1%
Quartier du Vermandois
29.5%
70.5%
Quartier du faubourg d'Isle
58.2%
41.8%
Quartier du Centre−Ville
66.4%
32.4%
1.2%
Quartier de Neuville
89.0%
10.6%
0.3%
Quartier de l'Europe
86.8%
13.0%
0.2%
OMISSY
73.4%
25.2%
1.4%
HARLY
96.1%
3.9%
Quartier
adulte
jeune
senescent
vieux
Stade
% d'arbres
100
75
50
25

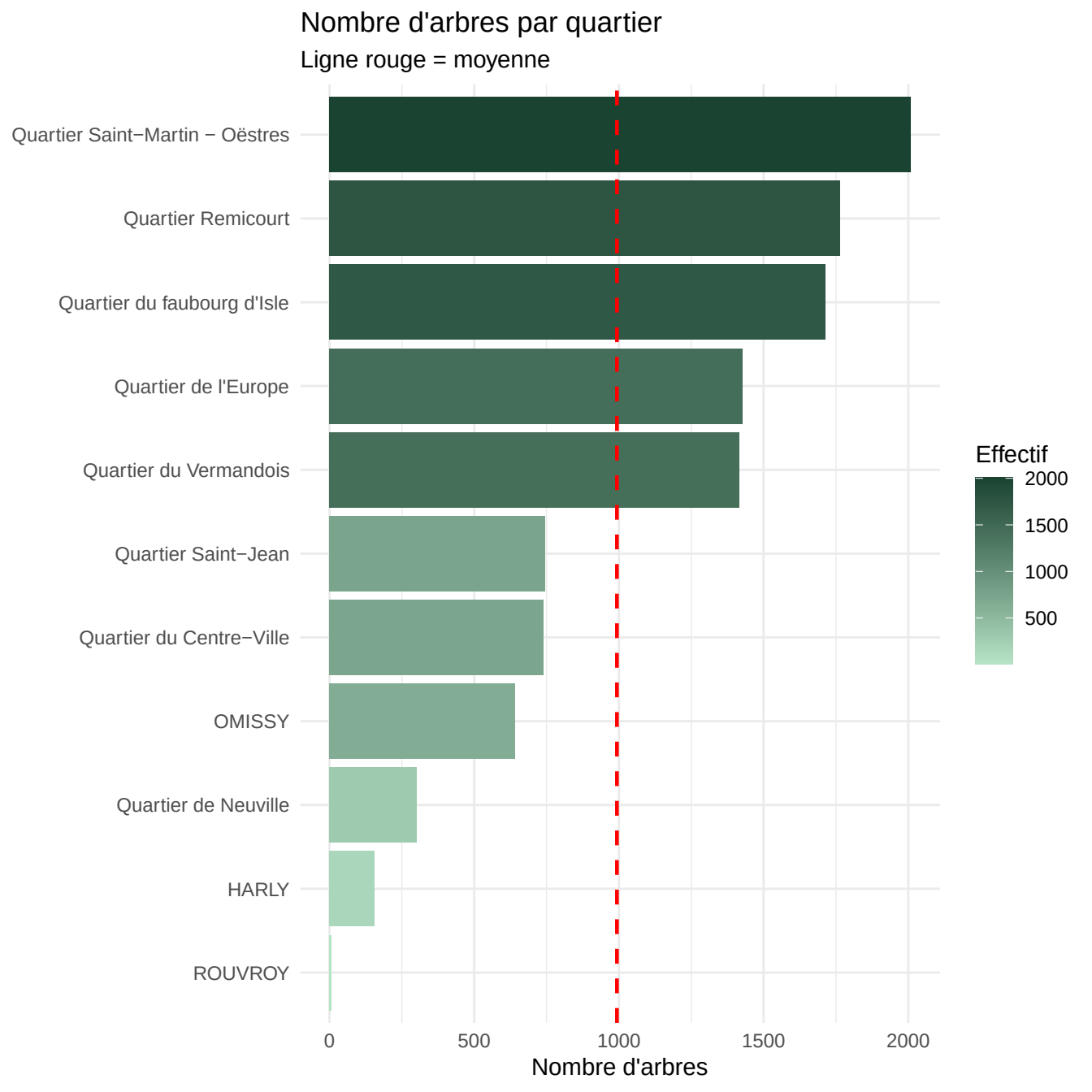
Nombre d'arbres par quartier
Ligne rouge = moyenne
Quartier Saint−Martin − Oëstres
Quartier Remicourt
Quartier du faubourg d'Isle
Quartier de l'Europe
Quartier du Vermandois
Quartier Saint−Jean
Quartier du Centre−Ville
OMISSY
Quartier de Neuville
HARLY
ROUVROY
0
500
1000
1500
2000
Nombre d'arbres
Effectif
2000
1500
1000
500

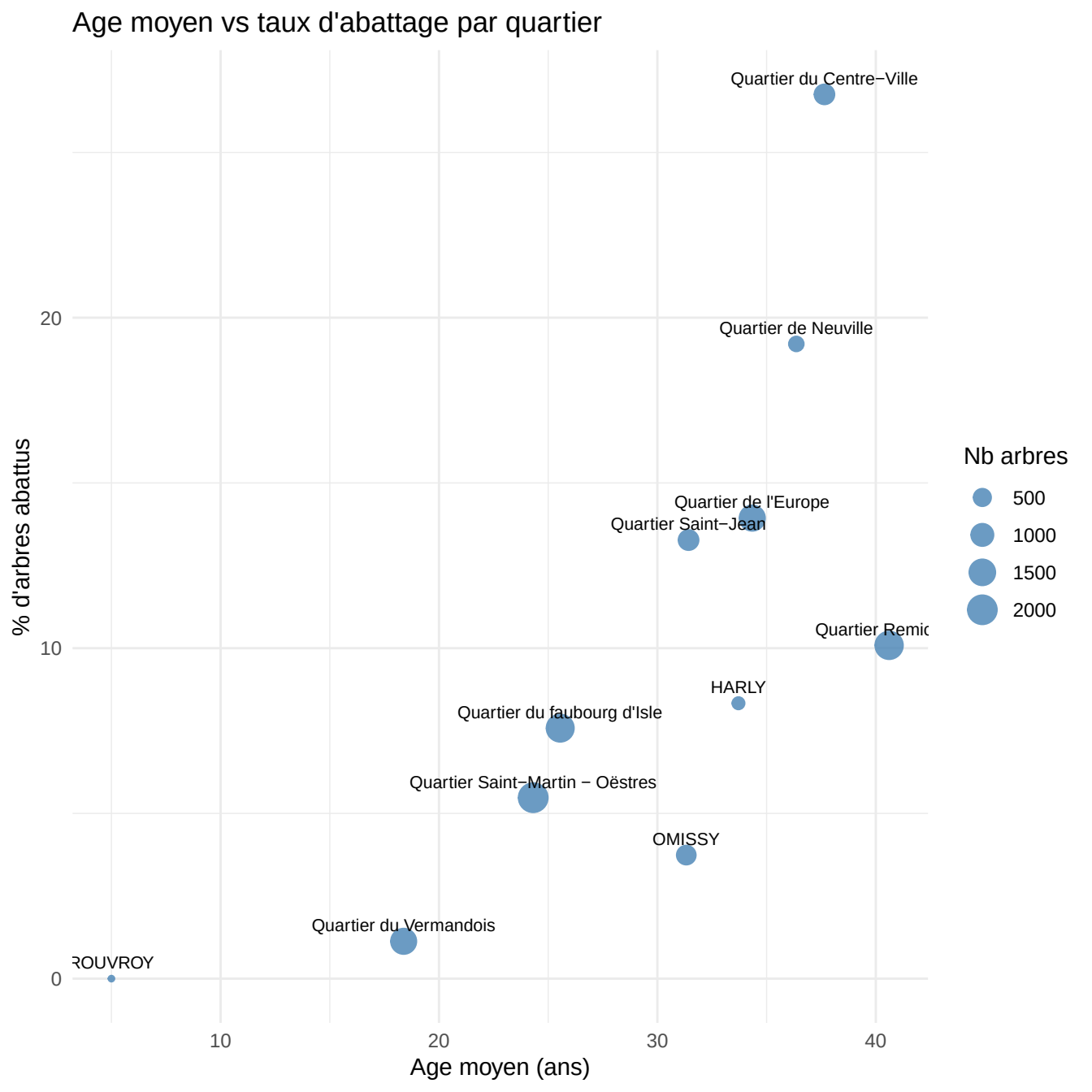
Age moyen vs taux d'abattage par quartier
Quartier du Centre−Ville
Quartier de Neuville
Quartier de l'Europe
Quartier Saint−Jean
Quartier Remic
HARLY
Quartier du faubourg d'Isle
Quartier Saint−Martin − Oëstres
OMISSY
Quartier du Vermandois
ROUVROY
% d'arbres abattus
0
10
20
10
20
30
40
Age moyen (ans)
Nb arbres
500
1000
1500
2000